PLANO DE AERÓDROMO-OACI

431807N
0082238W

ELEV 101 m

TWR 118.305 C
GMC 121.705 C

A CORUÑA

RWY	DIRECCIÓN DIRECTION	THR	RESISTENCIA STRENGTH
03	032°	431730.13N 0082308.72W	RWY: PCN 72/F/B/W/T EXC PLATAFORMA DE VIRAJE INTERMEDIA // INTERMEDIATE TURNING PAD PCN 68/F/C/W/T TWY N: PCN 47/F/B/W/T S: PCN 97/F/A/W/T NA: INFO NO AVBL APN: RAMPA // RAMP 0: PCN 95/R/D/W/T RAMPA // RAMP 1: PCN 90/R/C/W/T
21	212°	431830.94N 0082218.81W	

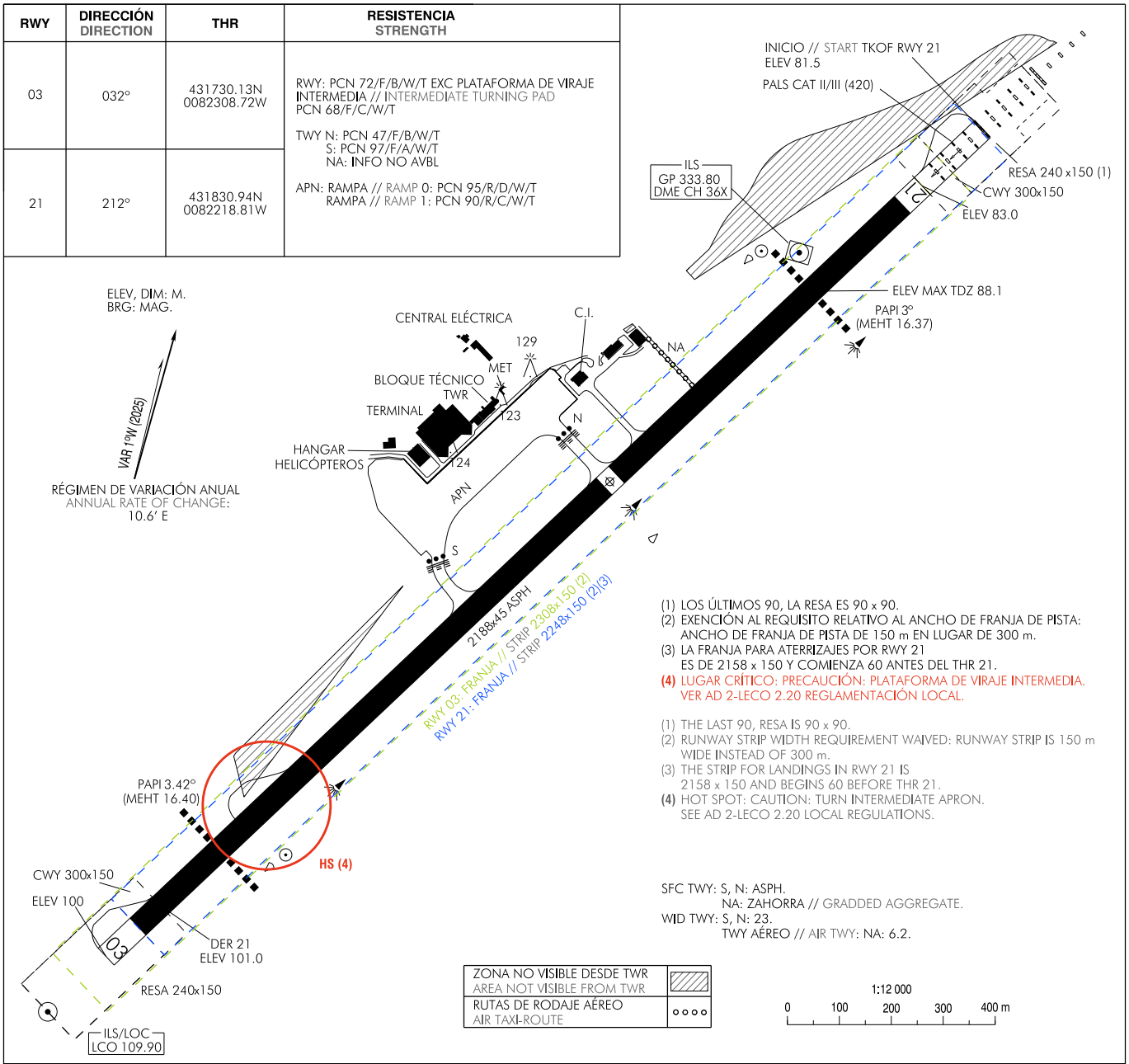

(1) LOS ÚLTIMOS 90, LA RESA ES 90 x 90.
(2) EXENCIÓN AL REQUISITO RELATIVO AL ANCHO DE FRANJA DE PISTA: ANCHO DE FRANJA DE PISTA DE 150 m EN LUGAR DE 300 m.
(3) LA FRANJA PARA ATERRIZAJES POR RWY 21 ES DE 2158 x 150 Y COMIENZA 60 ANTES DEL THR 21.
(4) LUGAR CRÍTICO: PRECAUCIÓN: PLATAFORMA DE VIRAJE INTERMEDIA. VER AD 2-LECO 2.20 REGLAMENTACIÓN LOCAL.

(1) THE LAST 90, RESA IS 90 x 90.
(2) RUNWAY STRIP WIDTH REQUIREMENT WAIVED: RUNWAY STRIP IS 150 m WIDE INSTEAD OF 300 m.
(3) THE STRIP FOR LANDINGS IN RWY 21 IS 2158 x 150 AND BEGINS 60 BEFORE THR 21.
(4) HOT SPOT: CAUTION: TURN INTERMEDIATE APRON. SEE AD 2-LECO 2.20 LOCAL REGULATIONS.

SFC TWY: S, N: ASPH.
NA: ZAHORRA // GRADDED AGGREGATE.
WID TWY: S, N: 23.
TWY AÉREO // AIR TWY: NA: 6.2.

SGL RWY & TWY

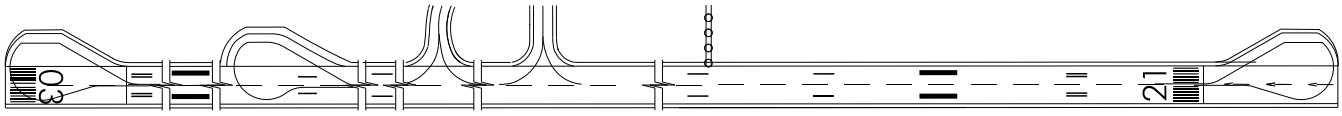

LGT RWY & TWY

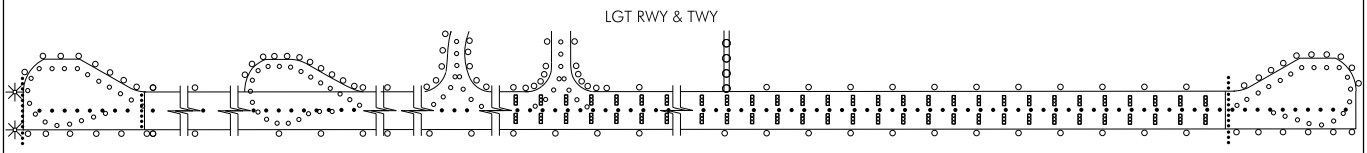

CAMBIOS: LUGAR CRÍTICO.
CHANGES: HOT SPOT.