CARTA DE APROXIMACIÓN
POR INSTRUMENTOS-OACI

ELEV AD
1998 ft
VAR 0° (2020)

APP 134.955 C
128.700 MHz
127.100 MHz
127.505 C

TWR 118.155 C
ATIS 118.255 C

MADRID/Adolfo Suárez
Madrid-Barajas
ILS W
RWY 32L

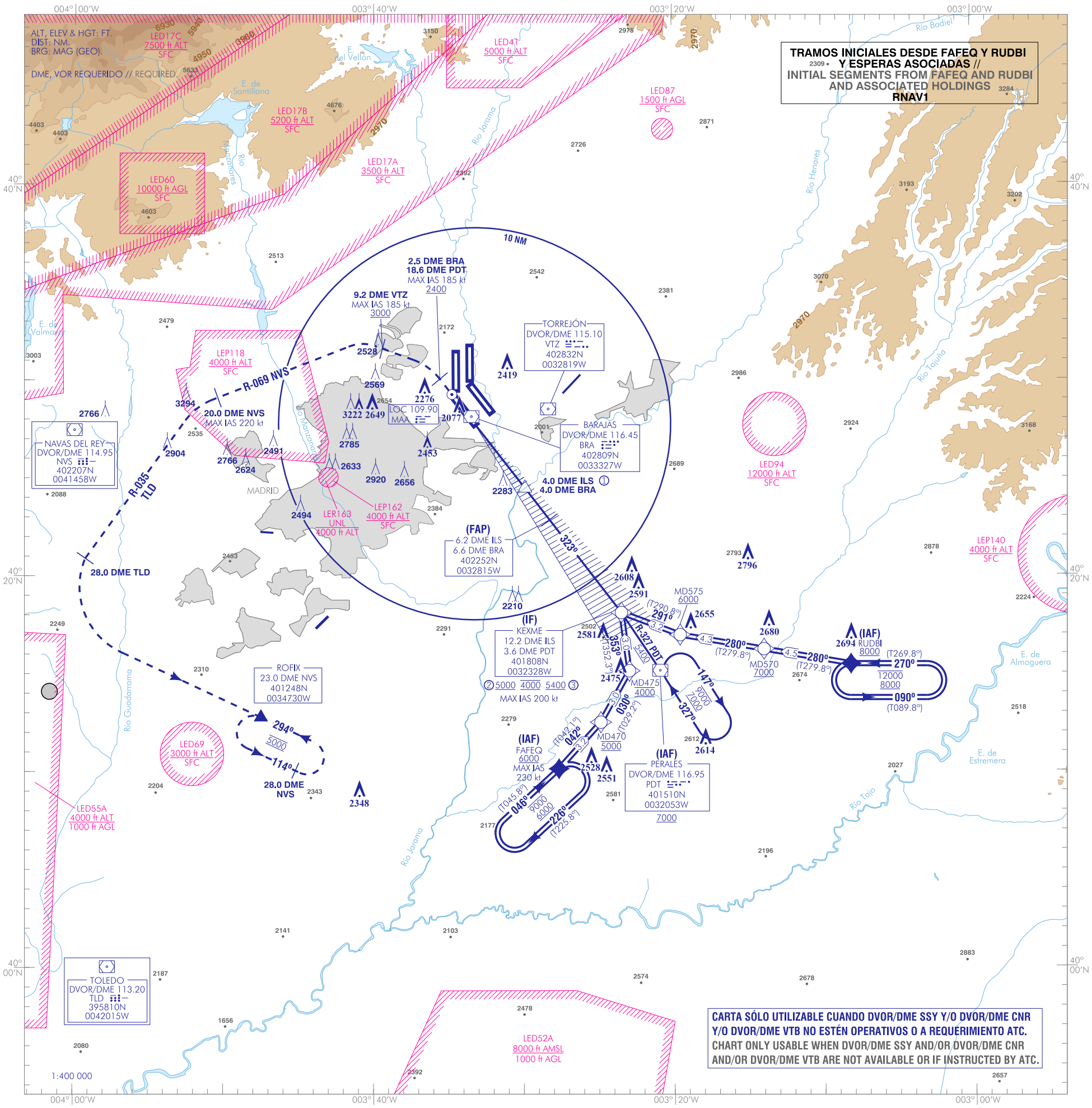

FRUSTRADA: SUBIR EN RUMBO DE PISTA HASTA 2.5 DME BRA/18.6 DME PDT PARA CRUZARLO A 2400 O SUPERIOR. VIRAR A LA IZQUIERDA (IAS MAX 185 kt) PARA SEGUIR R-290 VTZ HASTA CRUZAR 9.2 DME VTZ A 3000 O SUPERIOR. VIRAR A LA IZQUIERDA (IAS MAX EN VIRAJE 185 kt) PARA INTERCEPTAR Y SEGUIR R-069 NVS HASTA 20.0 DME NVS. VIRAR A LA IZQUIERDA (IAS MAX 220 kt) PARA INTERCEPTAR Y SEGUIR R-035 TLD HASTA 28.0 DME TLD. VIRAR A LA IZQUIERDA PARA INTERCEPTAR Y SEGUIR R-114 NVS DIRECTO A ROFIX PARA INTEGRARSE A LA ESPERA A 5000. DURANTE LA MANIOBRA DE APCH FRUSTRADA, NO SUPERAR 5000.

MISSED APCH: CLIMB ON RUNWAY HEADING UP TO 2.5 DME BRA/18.6 DME PDT TO CROSS IT AT 2400 OR ABOVE. TURN LEFT (MAX IAS 185 kt) TO FOLLOW R-290 VTZ, TO CROSS 9.2 DME VTZ AT 3000 OR ABOVE. TURN LEFT (MAX TURNING IAS 185 kt) TO INTERCEPT AND FOLLOW R-069 NVS UP TO 20.0 DME NVS. TURN LEFT (MAX IAS 220 kt) TO INTERCEPT AND FOLLOW R-035 TLD UP TO 28.0 DME TLD. TURN LEFT TO INTERCEPT AND FOLLOW R-114 NVS DIRECT TO ROFIX TO JOIN THE HOLDING AT 5000. DO NOT OVERSHOOT DURING THE MISSED APCH MANOEUVRE.

NOTAS:
① PUNTO DE NOTIFICACIÓN A PETICIÓN, OBLIGATORIO EN LVP.
② PARA TRANSICIONES DESDE RUDBI (IAF).
③ PARA TRANSICIONES DESDE PDT (IAF).
- PUEDEN ESTAR EN USO APROXIMACIONES PARALELAS SIMULTANEAS A RWY 32L/32R. VER AD 2-LEMD CASILLA 22.

NOTES:
① REPORTING POINT ON REQUEST, COMPULSORY UNDER LVP.
② FOR TRANSITIONS FROM RUDBI (IAF).
③ FOR TRANSITIONS FROM PDT (IAF).
- SIMULTANEOUS PARALLEL APPROACHES TO RWY 32L/32R MAY BE IN USE. SEE AD 2-LEMD ITEM 22.

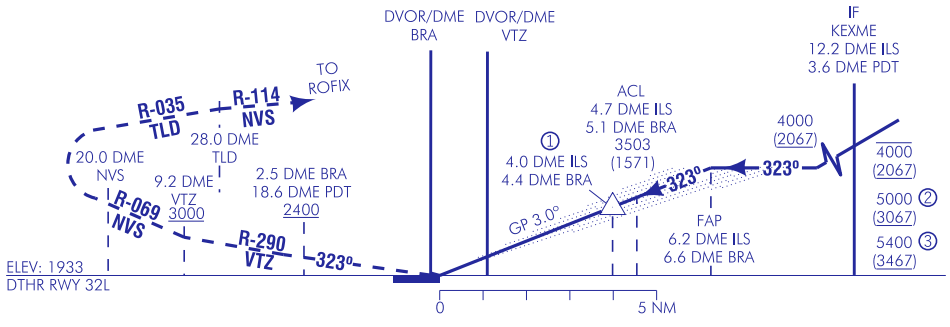

HGT REF ELEV DTHR RWY 32L

OCA/H		A	B	C	D
STA	CAT I	2183 (250)	2195 (262)	2203 (270)	2214 (281)
	CAT II	(148)	(165)	(177)	(191)
En circuito (H) sobre / Circling (H) over 1998		2720 (730)	2860 (870)	3280 (1290)	3620 (1630)

GS	kt	80	100	120	140	160	180
FAP-THR: 6.2 NM	min:s	4:40	3:44	3:06	2:40	2:20	2:04
FAF-MAPT:	min:s						
ROD: 5.2 %	ft/min	425	531	637	743	849	955

ALT/HGT DME (ILS) FNA													
14	13	12	11	10	9	8	7	6	5	4	3	2	1
								3930 (2000)	3610 (1670)	3280 (1350)	2960 (1020)	2630 (700)	2310 (380)

ILS RDH 54 | TA 13000

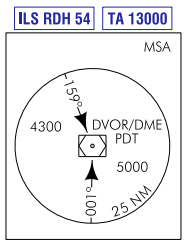

CAMBIOS: CORRECCIÓN OCA/H CAT I D, CAJA PBN, OBSTÁCULOS.
CHANGES: OCA/H CAT I D CORRECTION, PBN BOX, OBSTACLES.

INTENCIONADAMENTE EN BLANCO
INTENTIONALLY BLANK

MADRID/Adolfo Suárez Madrid-Barajas AD

REQUISITOS DE LA BASE DE DATOS AERONÁUTICA
AERONAUTICAL DATABASE REQUIREMENTS

PROCEDIMIENTOS DE APROXIMACIÓN POR INSTRUMENTOS // INSTRUMENT APPROACH PROCEDURES

ILS W RWY 32L

PUNTO POINT	LAT	LONG	AZIMUT VERDADERO TRUE BEARING	DISTANCIA DME DME DISTANCE (NM)
DVOR/DME PDT (IAF)	401510.5N	0032052.9W	-	-
KEXME (IF)	401807.8N	0032327.8W	326.23º (PDT)	3.56 DME PDT
→ FAP	402252.1N	0032815.1W	142.20º (LOC MAA)	6.21 DME ILS
ROFIX	401247.9N	0034729.9W	113.75º (NVS)	22.98 DME NVS
Aproximación final de precisión - Pendiente (Ángulo de descenso) // Precision final approach - Slope (Descent angle)				5.24% (3.00º)

COORDENADAS WAYPOINTS // WAYPOINTS COORDINATES	
WPT	COORD
FAFEQ (IAF)	401009.8N 0032738.5W
KEXME (IF)	401807.8N 0032327.8W
MD470	401232.0N 0032450.9W
MD475	401509.3N 0032256.3W
MD570	401615.4N 0031357.6W
MD575	401659.5N 0031933.0W
RUDBI (IAF)	401529.4N 0030810.0W

DESCRIPCIÓN TABULAR DEL PROCEDIMIENTO
PROCEDURE TABULAR DESCRIPTION

TRAMO INICIAL RNAV1 // RNAV1 INITIAL SEGMENT

Número de serie Serial number	Descriptor de trayectoria Path Terminator	Identificador de punto de recorrido Waypoint identifier	Sobrevuelo Fly-over	Curso/Derrota Course/Track ºM (ºT)	Variación magnética Magnetic variation	Distancia Distance (NM)	Dirección de viraje Turn direction	Altitud Altitude (ft)	Velocidad Speed (kt)	VPA/TCH (º/ft)	Especificación de navegación Navigation specification
FAFEQ (IAF) RNAV 1											
001	IF	FAFEQ	–	–	+0.4	–	–	+6000	-230	–	RNAV1
002	TF	MD470	–	042 (042.1)	+0.4	3.2	–	@5000	–	–	RNAV1
003	TF	MD475	–	030 (029.2)	+0.4	3.0	–	@4000	–	–	RNAV1
004	TF	KEXME	–	353 (352.3)	+0.4	3.0	–	@4000	-200	–	RNAV1
RUDBI (IAF) RNAV 1											
001	IF	RUDBI	–	–	+0.4	–	–	+8000	–	–	RNAV1
002	TF	MD570	–	280 (279.8)	+0.4	4.5	–	+7000	–	–	RNAV1
003	TF	MD575	–	280 (279.8)	+0.4	4.3	–	+6000	–	–	RNAV1
004	TF	KEXME	–	291 (290.8)	+0.4	3.2	–	+5000	-200	–	RNAV1

CIRCUITOS DE ESPERA // HOLDING PATTERN

Descriptor de trayectoria Path terminator	Identificador de punto de recorrido Waypoint identifier	Sobrevuelo Fly-over	Curso/Derrota Course/Track ºM (ºT)	Variación magnética Magnetic variation	Distancia/ Tiempo de alejamiento Distance/ Outbound time	Dirección de viraje Turn direction	Altitud MNM MNM altitude (ft)	Altitud MAX MAX altitude (ft)	Velocidad Speed (kt)	Especificación de navegación Navigation specification
HM	FAFEQ	–	046 (045.8)	+0.4	1 MIN	R	6000	9000	–	RNAV1
HM	RUDBI	–	270 (269.8)	+0.4	1 MIN	L	8000	12000	–	RNAV1

INTENCIONADAMENTE EN BLANCO
INTENTIONALLY BLANK