CARTE D'AERODROME - OACI-

30°15'50" N
005°51'12" W

ELEV 736 m

TWR 118.350

ZAGORA

RWY	DIRECTION	THR	FORCE PORTANTE
11	106°	30°16'12" N 005°52'39" W	PCR 760 /F/B/X/T
29	286°	30°15'45" N 005°50'51" W	

ALTITUDES ET DIMENSIONS EN METRES
RELEVEMENTS MAGNETIQUES

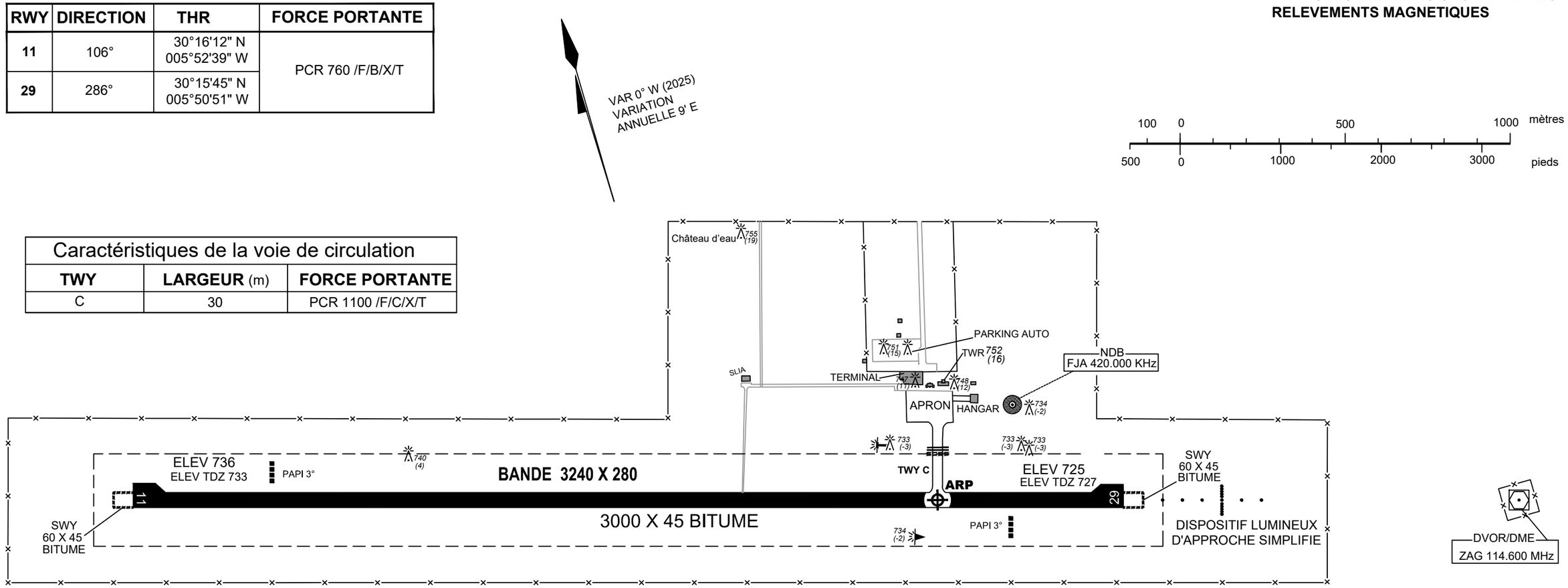

Caractéristiques de la voie de circulation		
TWY	**LARGEUR** (m)	**FORCE PORTANTE**
C	30	PCR 1100 /F/C/X/T

LEGENDE	
Manche à air (balisée)	
Feu de voie de circulation	
Pylône d'éclairage, Antenne	
Mur de clôture	
Voies de service	
Point d'attente avant piste	
Batiments	
Indicateur de direction d'atterrissage éclairé	

MARQUES RWY 11 / 29 ET SORTIE DE PISTE

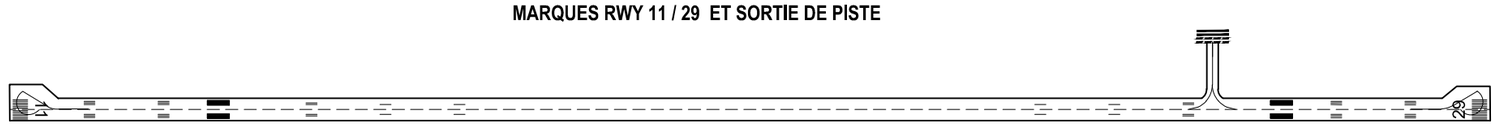
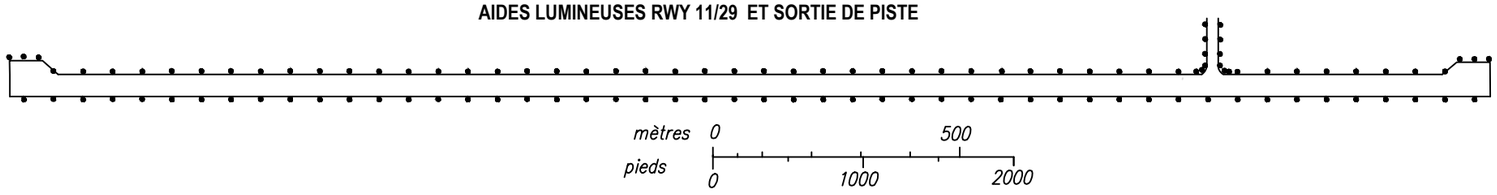
AIDES LUMINEUSES RWY 11/29 ET SORTIE DE PISTE