CARTE D'AERODROME -OACI

32° 30' 52" N
001° 58' 42" W

ELEV 1122m

TWR 118.000

BOUARFA

RWY	DIRECTION	THR	FORCE PORTANTE
09	89°	32° 30' 52" N 001° 59' 59" W	PCR 520 /F/B/X/U
27	269°	32° 30' 52" N 001° 57' 56" W	

Caractéristiques des voies de Circulation		
TWY	LARGEUR(m)	FORCE PORTANTE
TWY C	23	PCR 810 /F/B/X/T
TWY E	23	PCR 821 /F/B/X/T

ALTITUDES ET DIMENSIONS EN METRES
RELEVEMENTS MAGNETIQUES

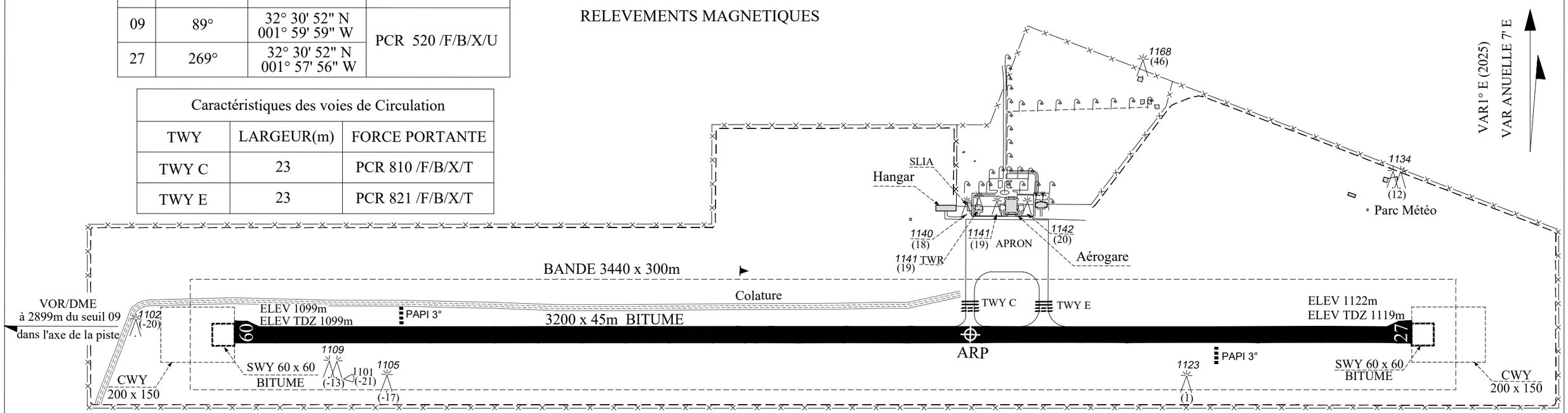

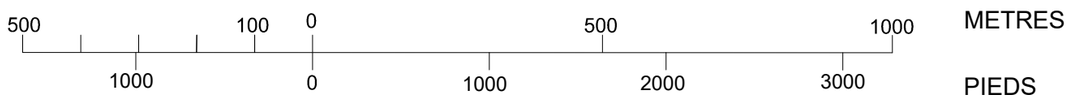
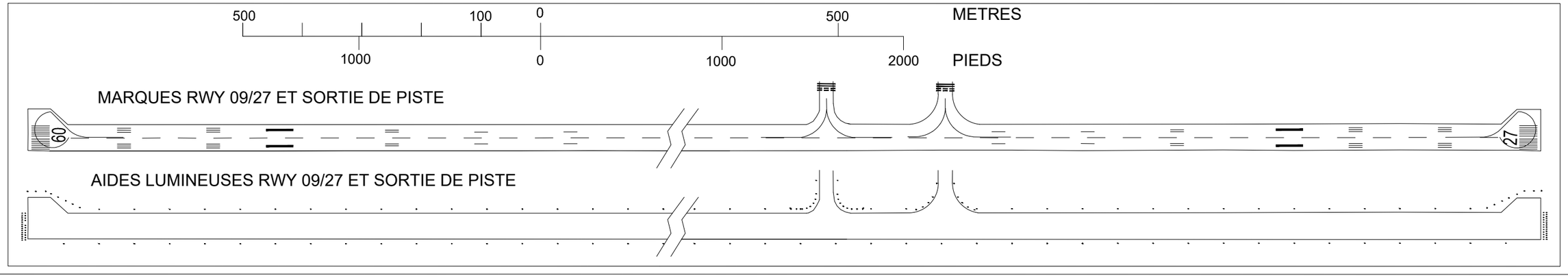
LEGENDE			
Feux des voies de circulation	• • • •	Pylône d'éclairage-Antenne	
Manche à air	▶	Lampadaire	
Bâtiments		Chemin de ronde	
Point d'attente avant piste		Palmiers	
Clôture	—×—×—	Colature	
Portée visuelle de piste (RVR)