CARTE D'AERODROME - OACI-

33°55'38"N
004°58'40"W

ELEV 578 m

TWR : 118.600
APP : 121.400

FES / SAISS

RWY	DIRECTION	THR - DTHR		FORCE PORTANTE
09	091°	THR	33°55'38"N 004°59'43"W	PCR 720 /F/C/X/T
27	271°	THR	33°55'38"N 004°57'38"W	
		DTHR	33°55'38"N 004°57'47"W	

ALTITUDES ET DIMENSIONS EN METRES
RELEVEMENTS MAGNETIQUES

VAR 1° W (2020)
VARIATION ANNUELLE 7' E

Caractéristiques des voies de circulation		
TWY	**LARGEUR**	**FORCE PORTANTE**
TWY L	7.5	5700 Kg/0.90 MPA
TWY E	23	PCR 660 /F/B/X/T
TWY C	23	PCR 840 /F/B/X/T
TWY W	23	PCR 750 /F/B/X/T
TWY N	25	PCR 770 /F/B/X/T
TWY P	23	PCR 840 /F/B/X/T

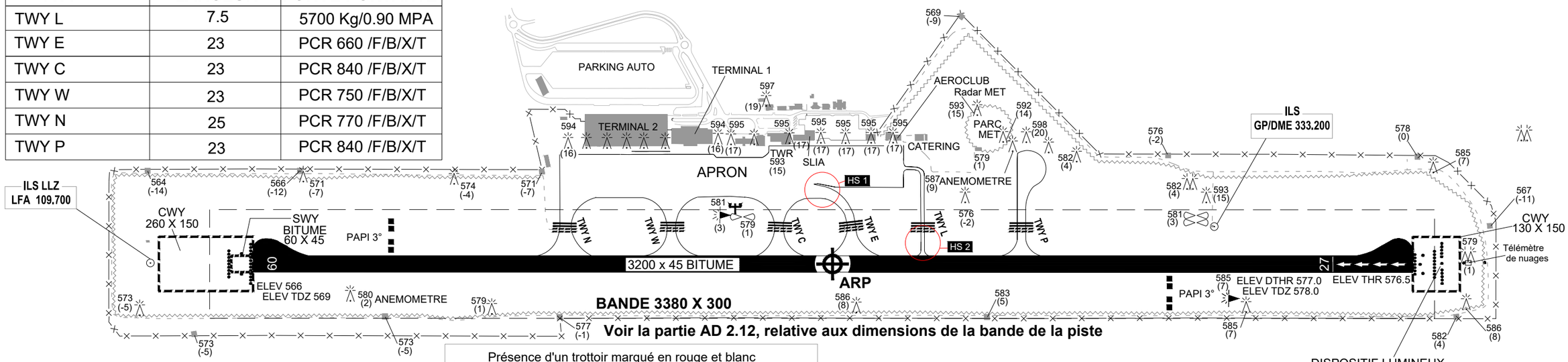

Voir la partie AD 2.12, relative aux dimensions de la bande de la piste

HS 1 — Présence d'un trottoir marqué en rouge et blanc séparant la bretelle ECHO et l'aire de trafic

HS 2
- La Sortie de la piste via le TWY L n'est pas autorisée.
- Le TWY L n'est autorisé que pour accéder à la piste d'envol uniquement de jour et seulement pour l'aviation légère.
- Risque de confusion avec TWY E.

100 0 500 1000 mètres
500 0 1000 2000 3000 pieds

LEGENDE

Feux (TWY, RWY)	
Manche à air (éclairée)	
Portée visuelle de piste (RVR)	
PAPI	
Marque de points d'attente avant piste	
Mur de clôture	
Chemin de ronde \ Piste	
Clôture grillagée	
Route	
Pylône d'éclairage, Antenne,...	
Diffusomètre	
Point chaud	HS
Construction	

MARQUES RWY 09/27 ET SORTIES DE PISTE

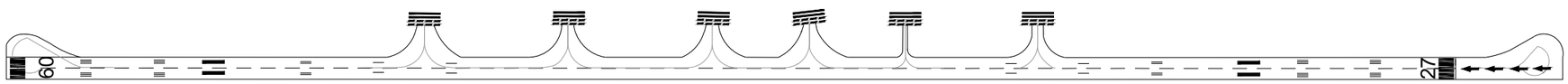
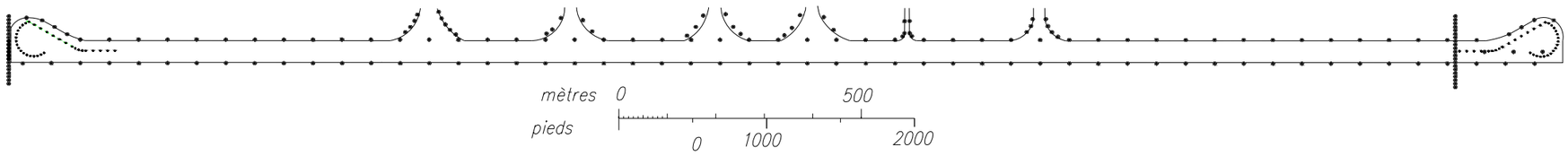
AIDES LUMINEUSES RWY 09/27 ET SORTIES DE PISTE