CARTE D'AERODROME - OACI-

23°43'06" N
015°55'55" W

ELEV 11 m

TWR 118.100

DAKHLA

RWY	DIRECTION	THR	FORCE PORTANTE
03	028°	23°42'21"N 015°56'15"W	BITUME PCR 775/F/A/X/T
21	208°	23°43'51"N 015°55'34"W	

ALTITUDES ET DIMENSIONS EN METRES
RELEVEMENTS MAGNETIQUES

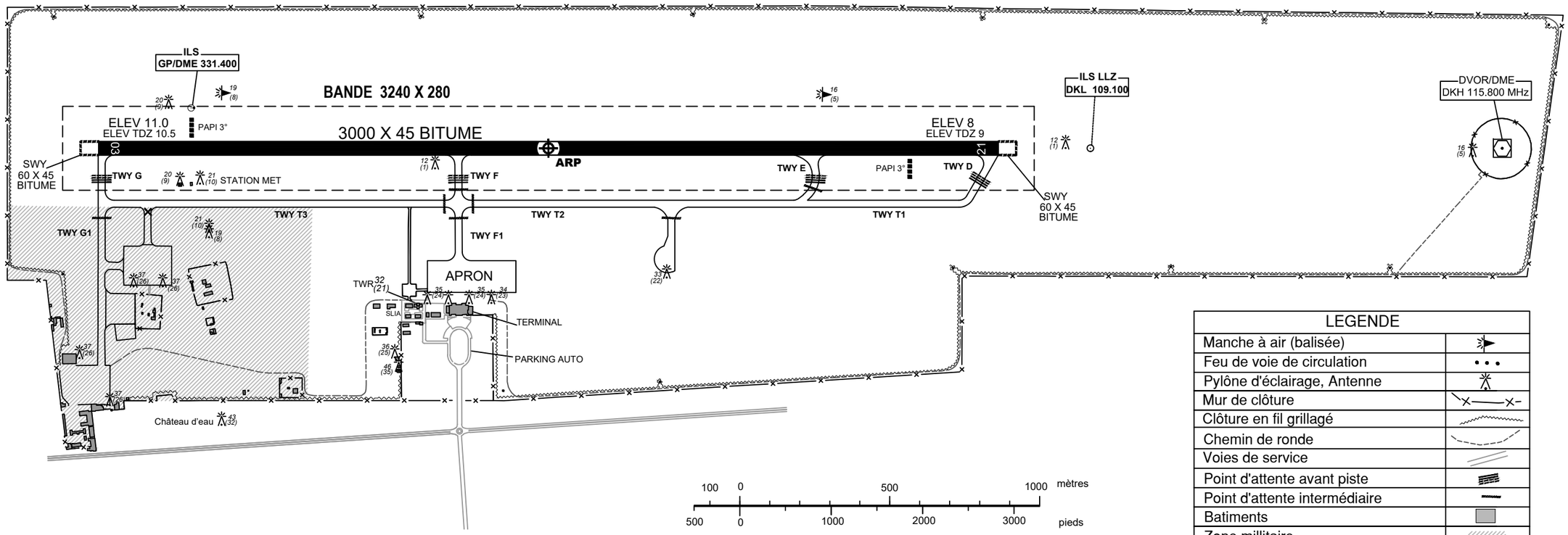

LEGENDE	
Manche à air (balisée)	
Feu de voie de circulation	
Pylône d'éclairage, Antenne	
Mur de clôture	
Clôture en fil grillagé	
Chemin de ronde	
Voies de service	
Point d'attente avant piste	
Point d'attente intermédiaire	
Batiments	
Zone millitaire	
TWY Fermé	×

Caractéristiques des voies de circulation		
TWY	**LARGEUR** (m)	**FORCE PORTANTE**
T1	23	PCR 775/F/A/X/T
T2		
F		
G1		
D		
T3		PCR 710/F/A/X/T
E		PCR 500/F/A/X/T
F1		PCR 570/F/A/X/T
G		PCR 750/F/A/X/T

MARQUES RWY 03 / 21 ET SORTIES DE PISTE

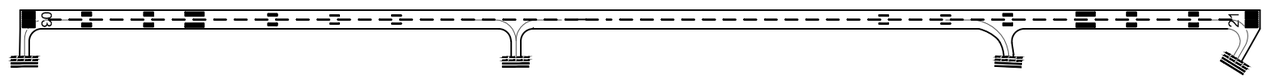

AIDES LUMINEUSES RWY 03/21 ET SORTIES DE PISTE

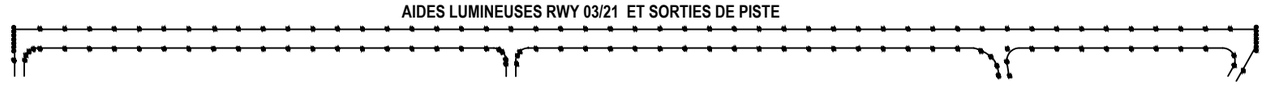

mètres 0 500
pieds 0 1000 2000