**CARTE D'AERODROME - OACI -** 31°23'57" N 009°40'59" W ELEV 128m TWR 118.250 APP 119.800

# ESSAOUIRA / Mogador

**ALTITUDES ET DIMENSIONS EN METRES**
**RELEVEMENTS MAGNETIQUES**

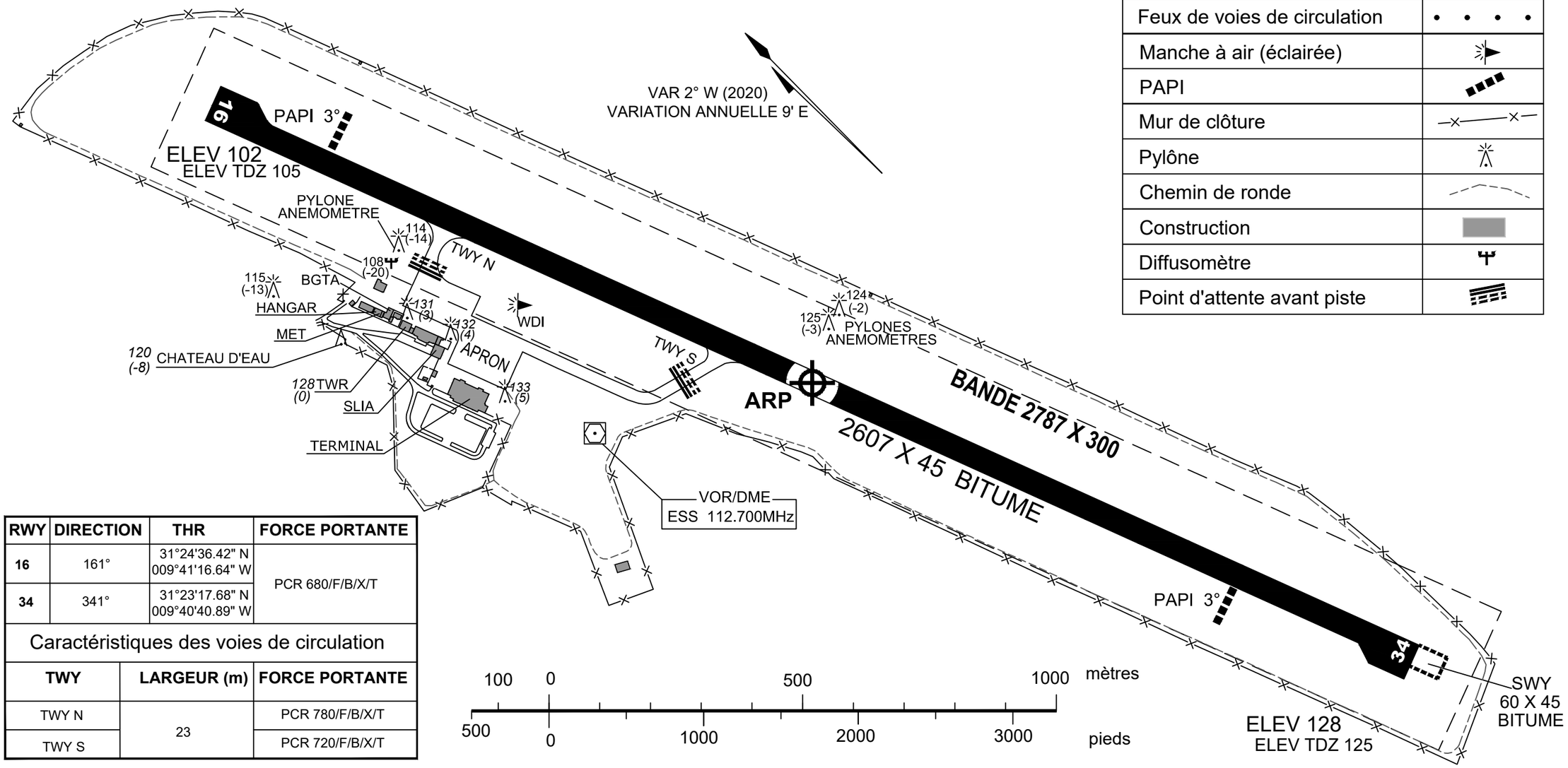


## LEGENDE

| | |
|---|---|
| Feux de voies de circulation | • • • • |
| Manche à air (éclairée) | |
| PAPI | |
| Mur de clôture | |
| Pylône | |
| Chemin de ronde | |
| Construction | |
| Diffusomètre | |
| Point d'attente avant piste | |

| RWY | DIRECTION | THR | FORCE PORTANTE |
|---|---|---|---|
| **16** | 161° | 31°24'36.42" N 009°41'16.64" W | PCR 680/F/B/X/T |
| **34** | 341° | 31°23'17.68" N 009°40'40.89" W | |

Caractéristiques des voies de circulation

| TWY | LARGEUR (m) | FORCE PORTANTE |
|---|---|---|
| TWY N | 23 | PCR 780/F/B/X/T |
| TWY S | | PCR 720/F/B/X/T |

**MARQUES RWY 16 / 34 ET SORTIES DE PISTE**

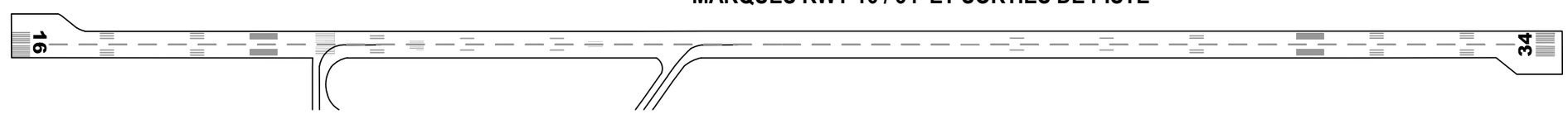

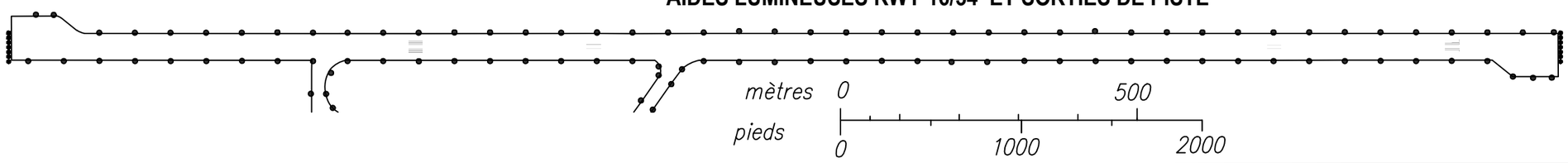
**AIDES LUMINEUSES RWY 16/34 ET SORTIES DE PISTE**