CARTE D'AERODROME - OACI

ARP
34°59'22"N
003°01'40"W

ELEV 181 m

TWR : 118.650
136.200

NADOR / EL AROUI

RWY	DIRECTION	THR	FORCE PORTANTE
08	078°	34°59'11" N 003°02'38" W	PCR 410/F/A/X/T
26	258°	34°59'31" N 003°00'42" W	

Caractéristiques des voies de circulation		
TWY	**LARGEUR (m)**	**FORCE PORTANTE**
TWY E	23	PCR 400/F/A/X/U
TWY W	23	

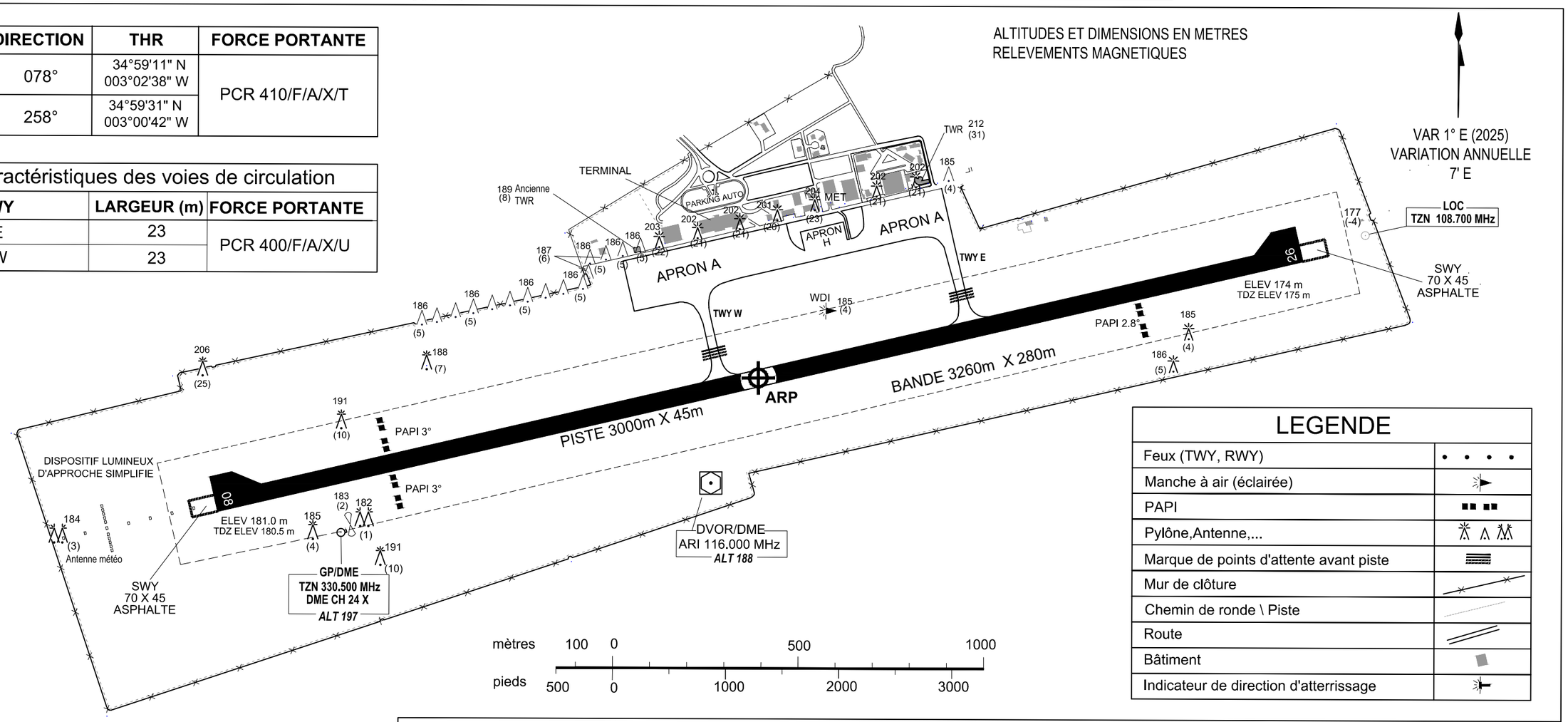

LEGENDE

Feux (TWY, RWY)	
Manche à air (éclairée)	
PAPI	
Pylône,Antenne,...	
Marque de points d'attente avant piste	
Mur de clôture	
Chemin de ronde \ Piste	
Route	
Bâtiment	
Indicateur de direction d'atterrissage	

MARQUES RWY 08/26 ET SORTIES DE PISTE

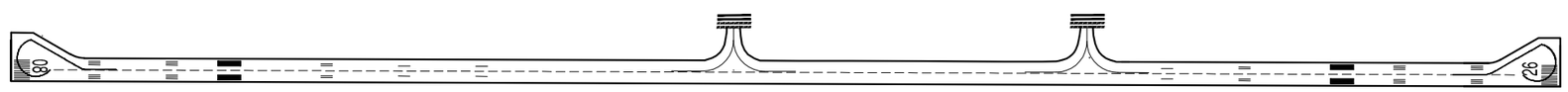
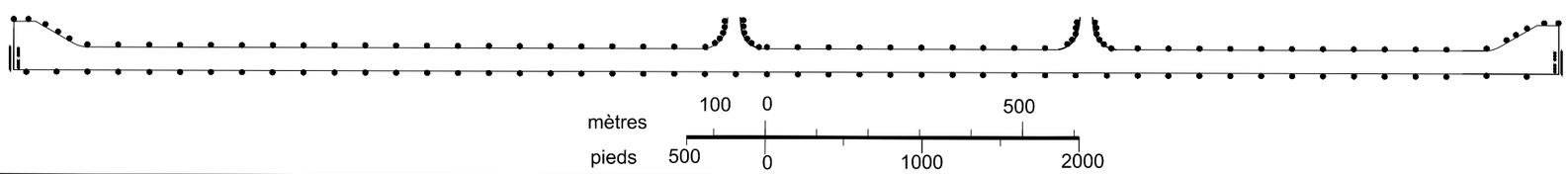
AIDES LUMINEUSES RWY 08/26 ET SORTIES DE PISTE