CARTE D'AERODROME - OACI- 35°10'47"N 003°50'24"W ELEV 34 m TWR 118.700 123.900

AL HOCEIMA/CHÉRIF EL IDRISSI

ALTITUDES ET DIMENSIONS EN METRES
RELEVEMENTS MAGNETIQUES

RWY	DIRECTION	THR / DTHR		FORCE PORTANTE
17	173°	THR	35°11'22" N 003°50'29" W	PCR 1325/F/D/X/T
		DTHR	35°11'19" N 003°50'29" W	
35	353°	THR	35°09'39" N 003°50'13" W	
		DTHR	35°09'58" N 003°50'16" W	

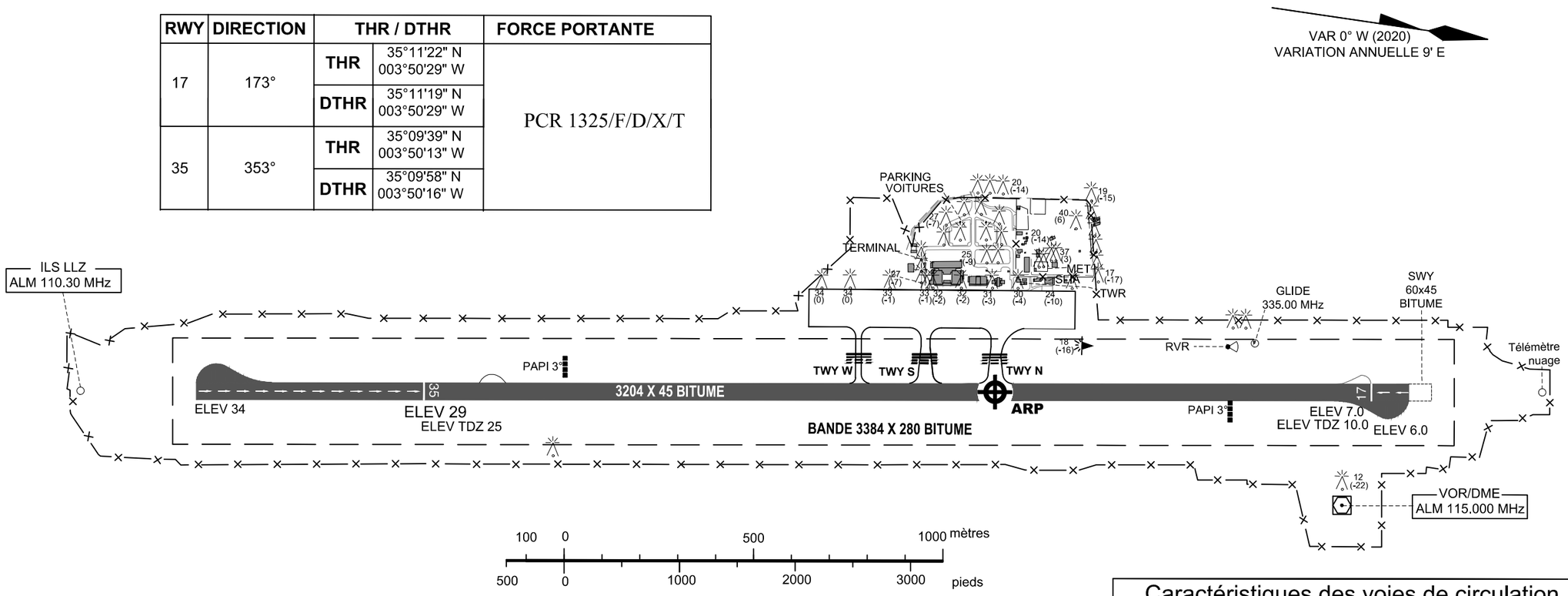

Caractéristiques des voies de circulation		
TWY	**LARGEUR** (m)	**FORCE PORTANTE**
N	23	PCR 1325/F/D/X/T
S		
W	15	

LEGENDE	
Manche à air (balisée)	
Feu de voie de circulation	
Pylône d'éclairage, Antenne	
Mur de clôture	
Chemin de ronde	
Voies de service	
Point d'attente avant piste	
PAPI	
Bâtiment	
RVR	

MARQUES RWY 17 /35 ET SORTIES DE PISTE

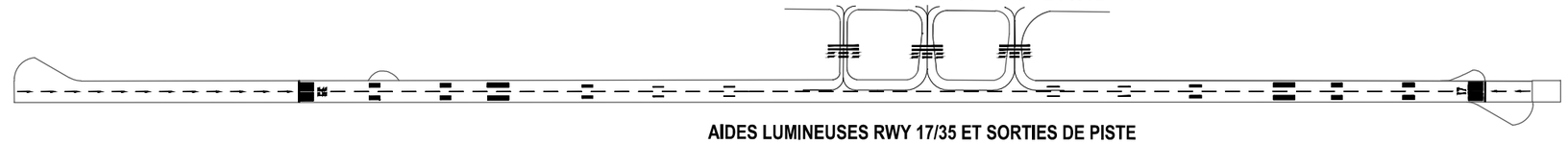
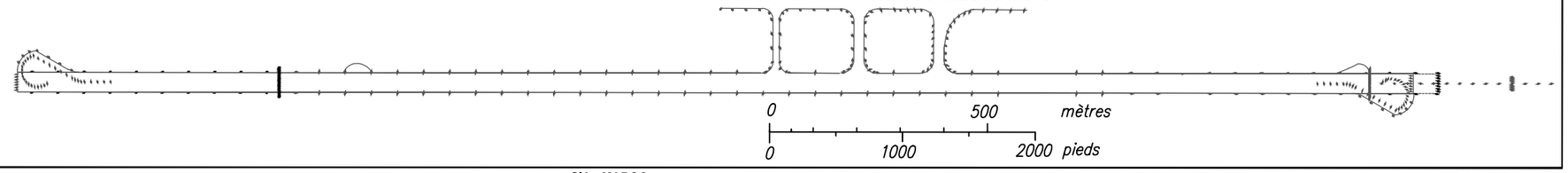
AIDES LUMINEUSES RWY 17/35 ET SORTIES DE PISTE