CARTE D'AERODROME - OACI-

ARP
35°43'54" N
005°55'16" W

ELEV 21 m

TWR 119.500 MHz
APP 121.200 MHz

TANGER / Ibn Batouta

ALTITUDES ET DIMENSIONS EN METRES
RELEVEMENTS MAGNETIQUES

RWY	DIRECTION	THR - DTHR		FORCE PORTANTE
10	097°	THR	35°44'00"N 005°56'25"W	BITUME PCR 920/F/C/X/T
28	277°	THR	35°43'47"N 005°54'07"W	
		DTHR	35°43'49"N 005°54'27"W	

CARACTERISTIQUES DES VOIES DE CIRCULATION

TWY	LARGEURS	FORCE PORTANTE
T1 - T2 - T3 - T4 - T5 A - B - C1 - C2 - D E - F	23	PCR 920/F/C/X/T

VAR 1° W (2020)
VAR ANNUELLE 9' E

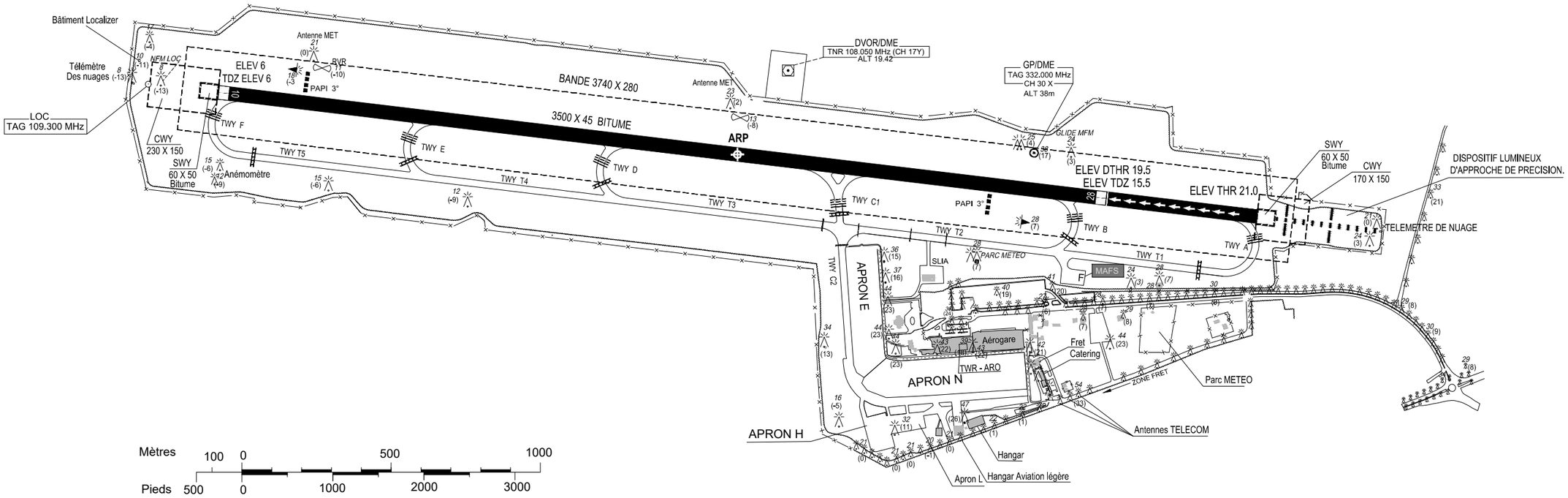

LEGENDE	
Manche à air (éclairée)	
Feux de voie de circulation	
Pylône d'éclairage, Antenne, Pylône balisé....	
Portée visuelle de piste (RVR)	
Mur de clôture	
Clôture grillage	
Point d'attente de circulation	
Point d'attente intermédiaire	
PAPI	
Bâtiments	

MAFS : Poste de stationnement réservé aux avions de lutte contre les feux des forêts

MARQUES RWY 10/28 ET SORTIES DE PISTE

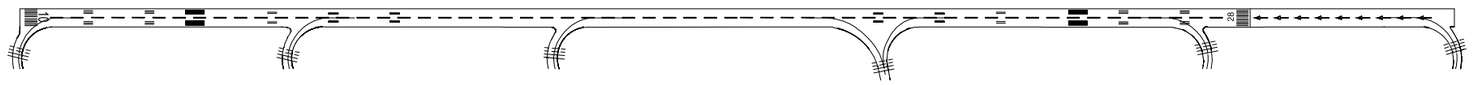
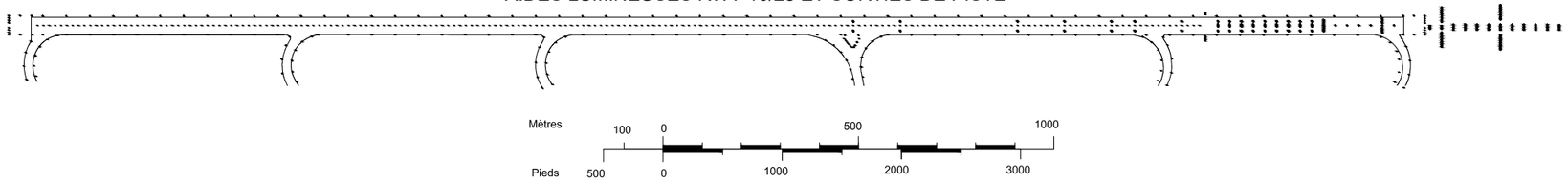
AIDES LUMINEUSES RWY 10/28 ET SORTIES DE PISTE